Interface principale

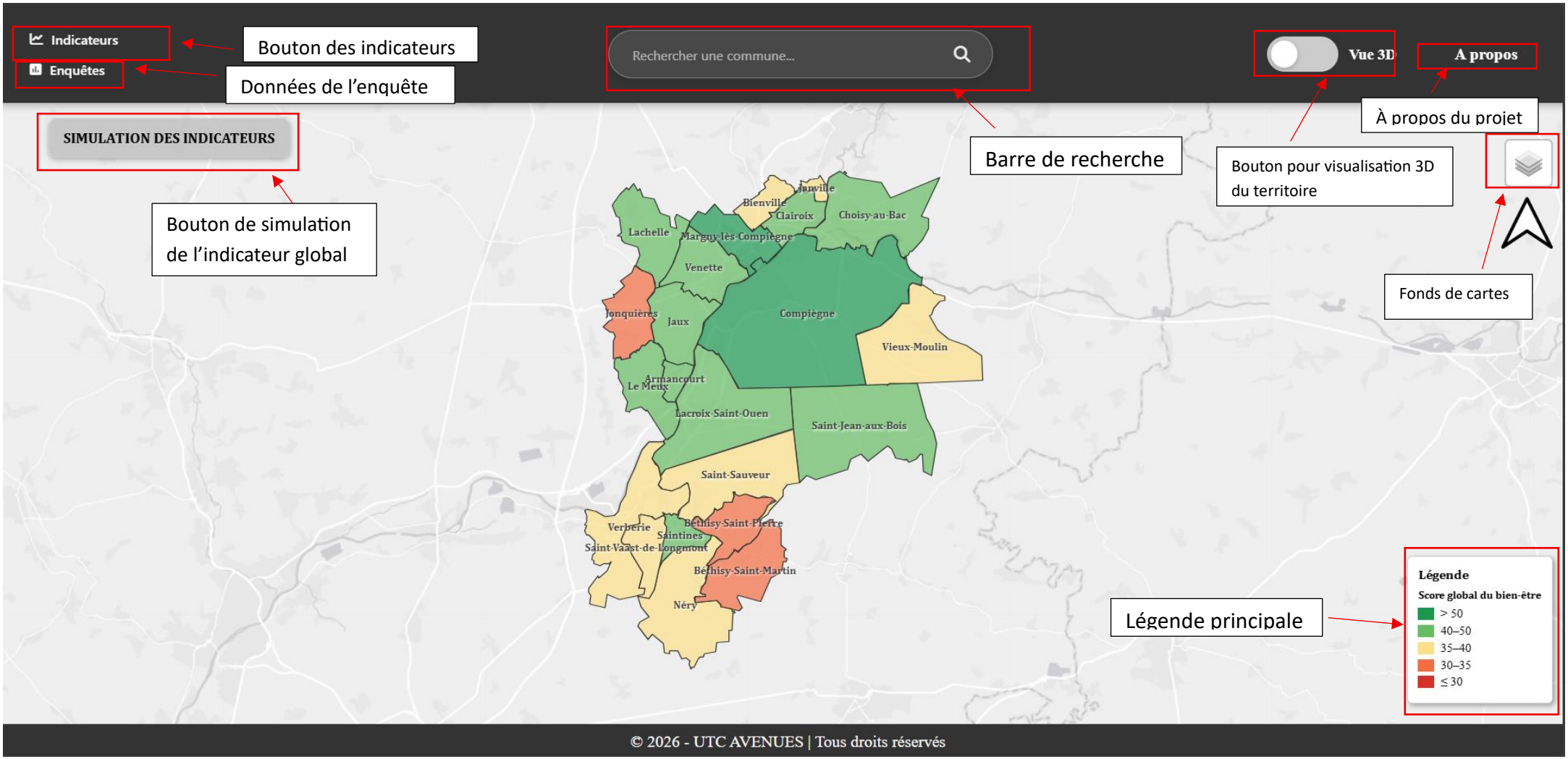

Informations sur une commune

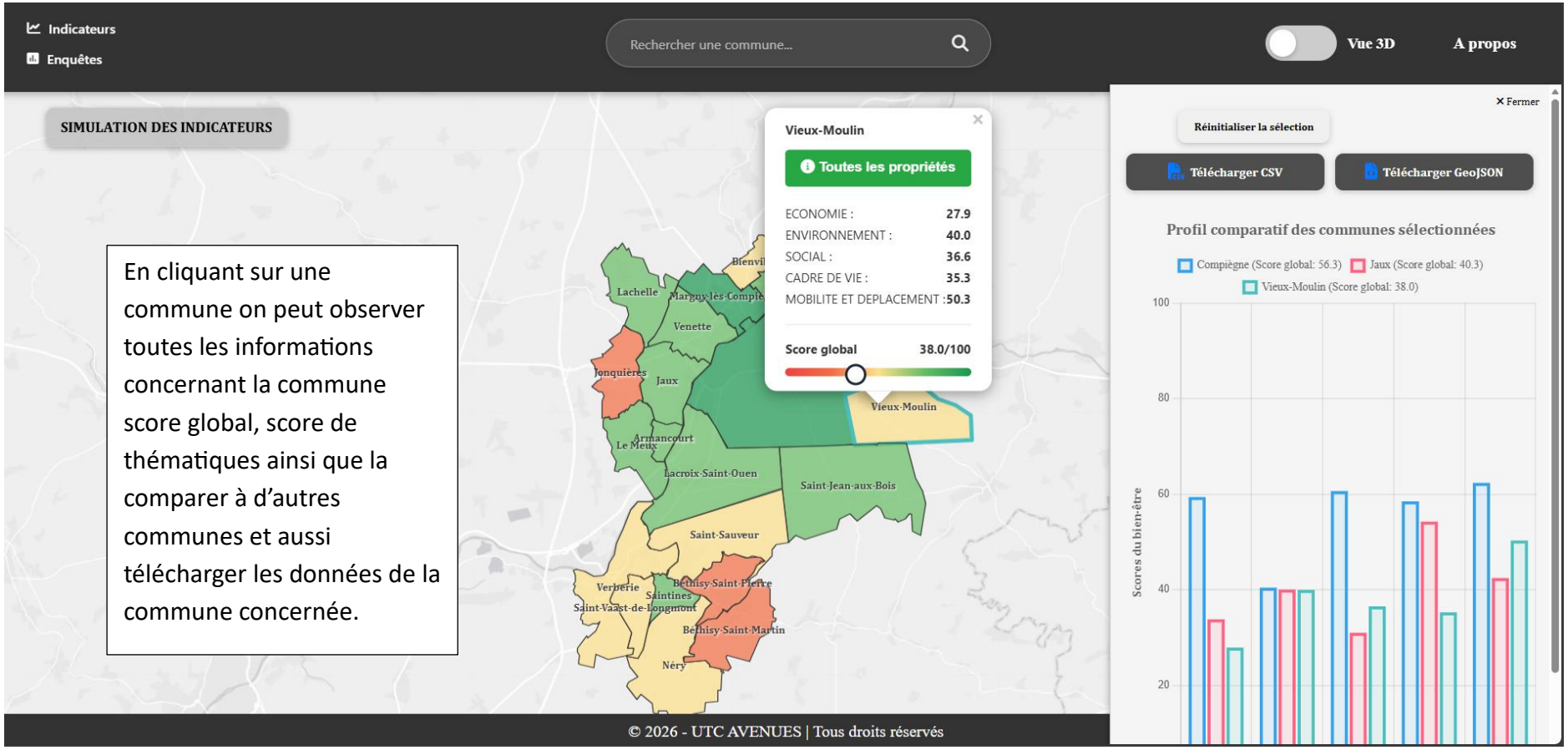

En cliquant sur une commune on peut observer toutes les informations concernant la commune score global, score de thématiques ainsi que la comparer à d'autres communes et aussi télécharger les données de la commune concernée.

Simulation du score

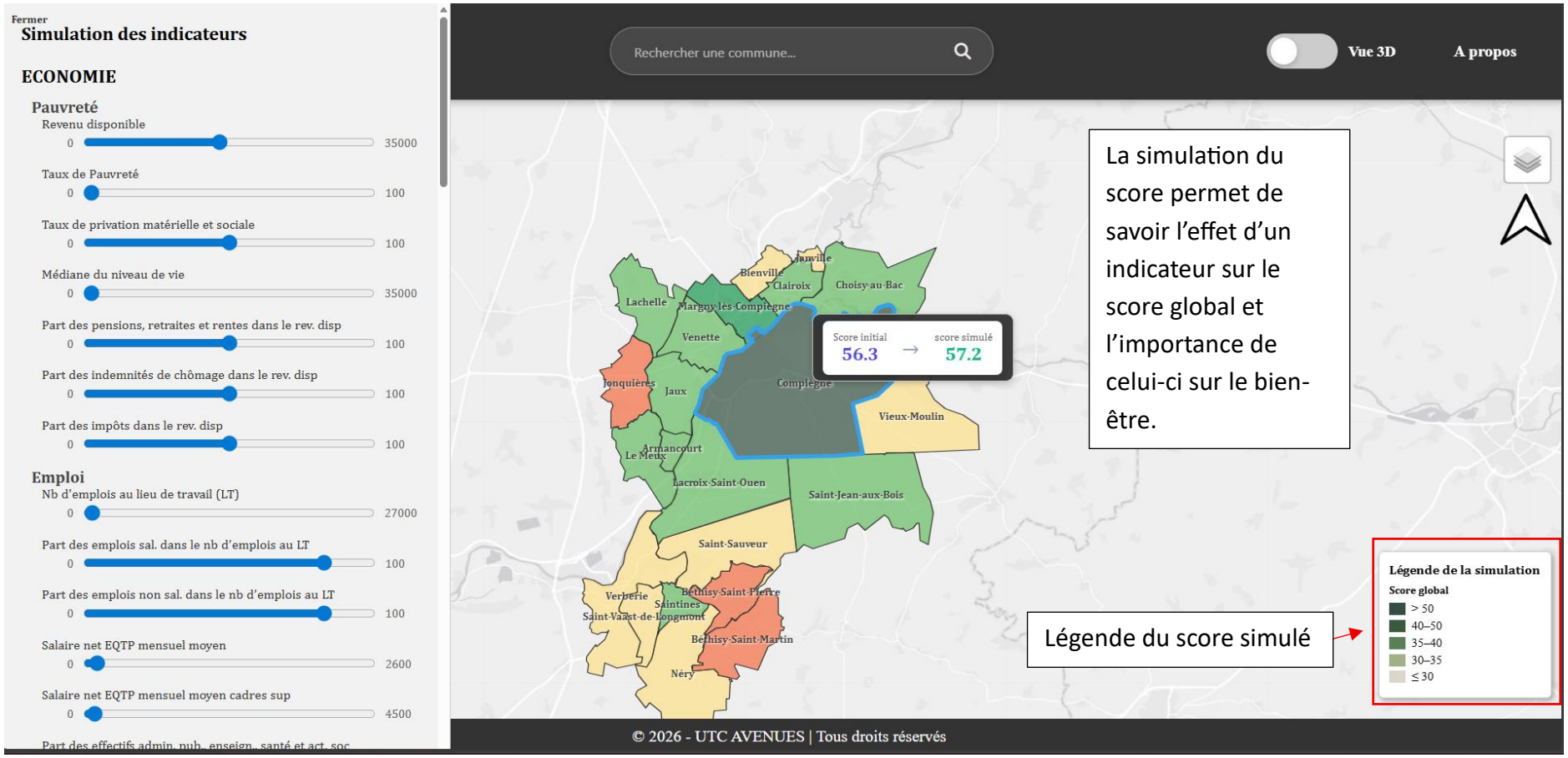

Barre de recherche

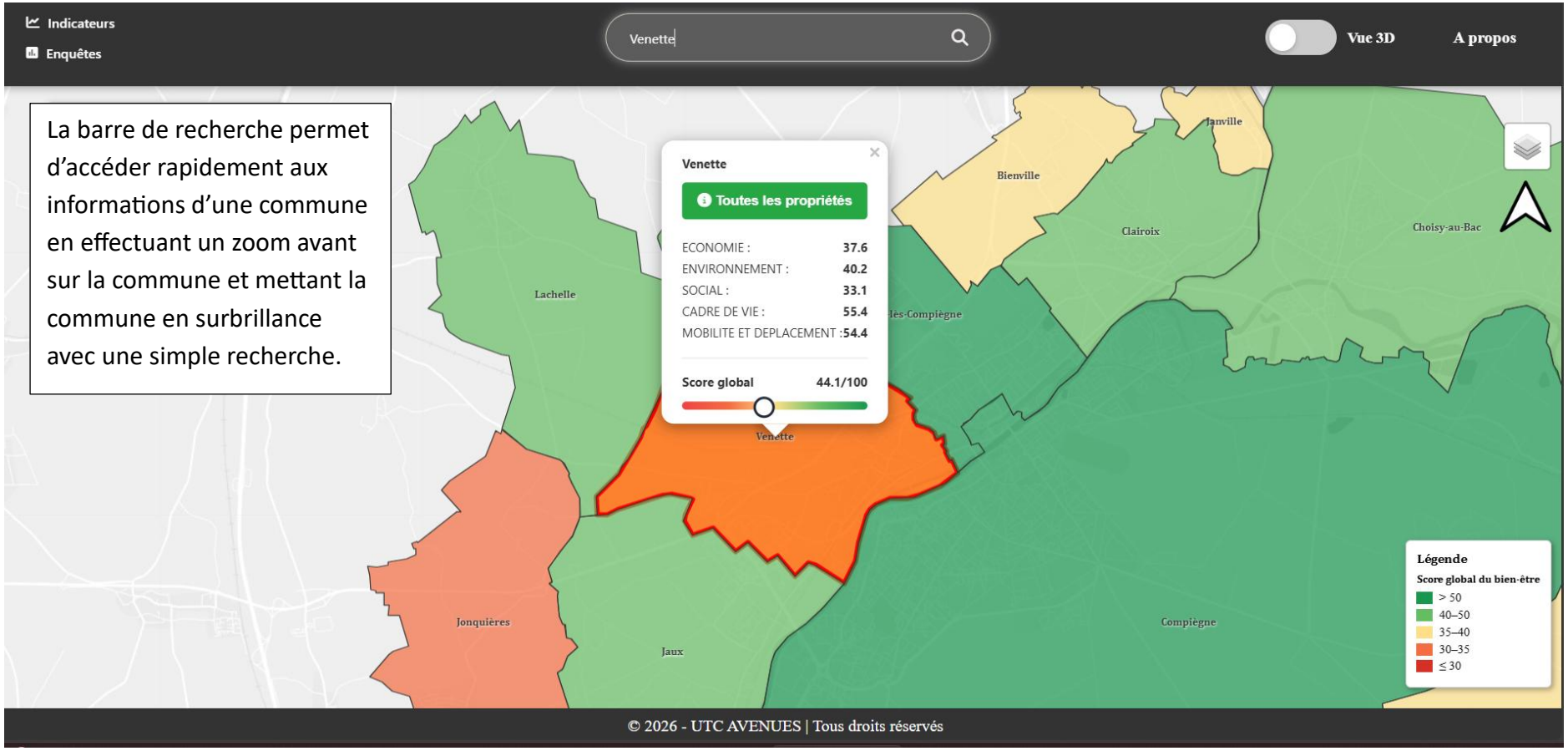

Indicateurs

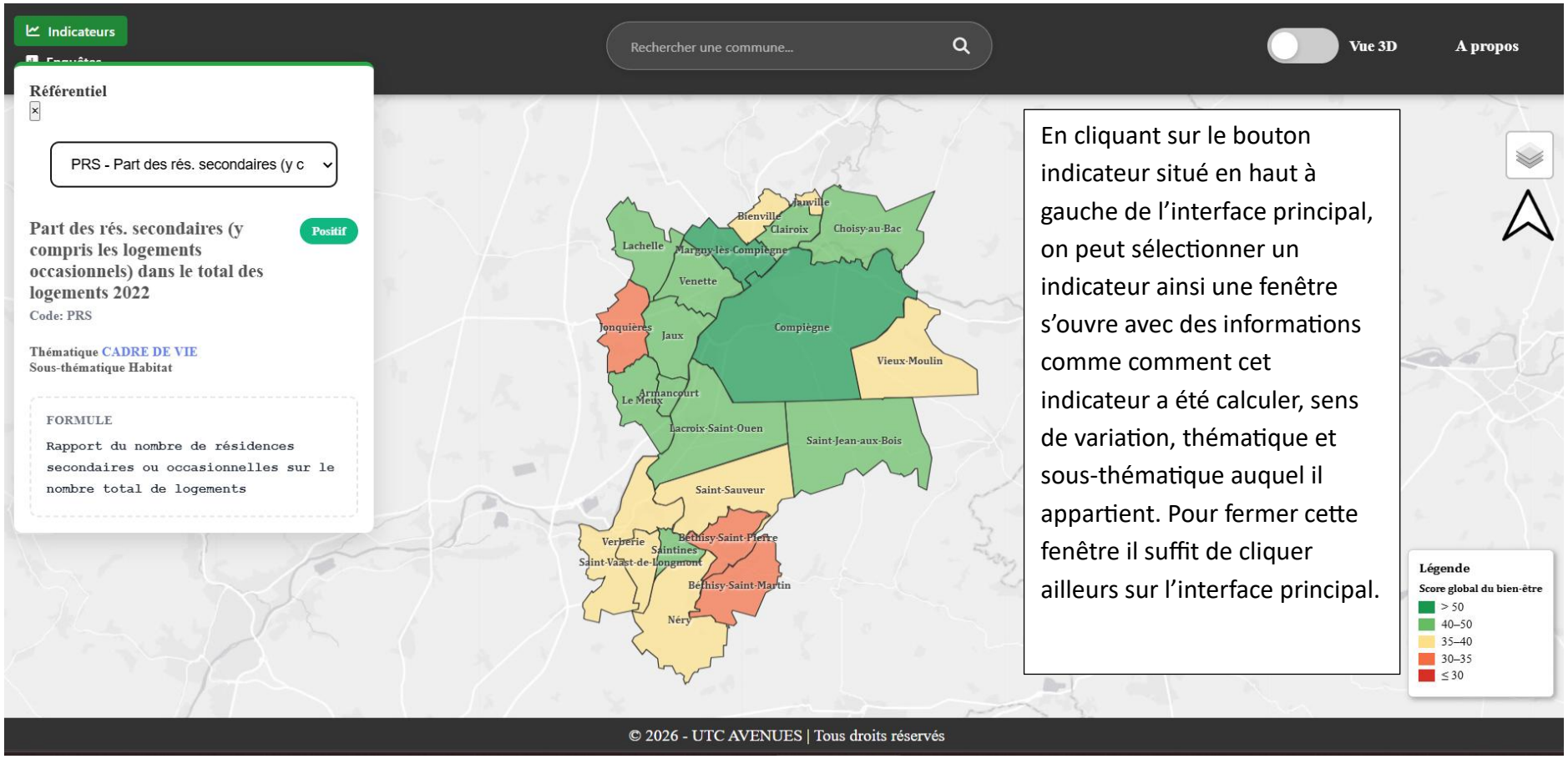

En cliquant sur le bouton indicateur situé en haut à gauche de l’interface principal, on peut sélectionner un indicateur ainsi une fenêtre s’ouvre avec des informations comme comment cet indicateur a été calculer, sens de variation, thématique et sous-thématique auquel il appartient. Pour fermer cette fenêtre il suffit de cliquer ailleurs sur l’interface principal.

Données de l’enquête sur Compiègne

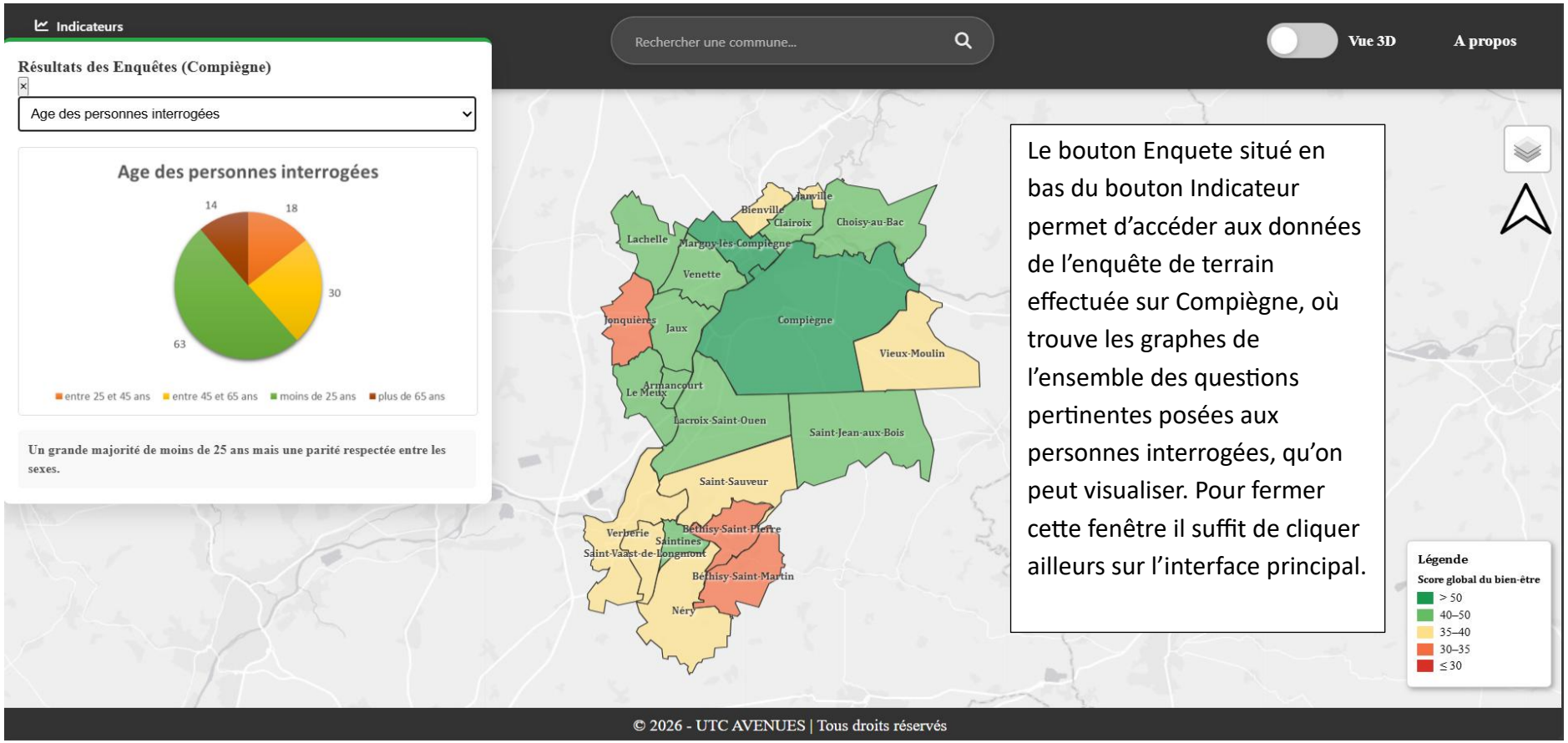

Le bouton Enquete situé en bas du bouton Indicateur permet d’accéder aux données de l’enquête de terrain effectuée sur Compiègne, où trouve les graphes de l’ensemble des questions pertinentes posées aux personnes interrogées, qu’on peut visualiser. Pour fermer cette fenêtre il suffit de cliquer ailleurs sur l’interface principal.

Fonds de cartes

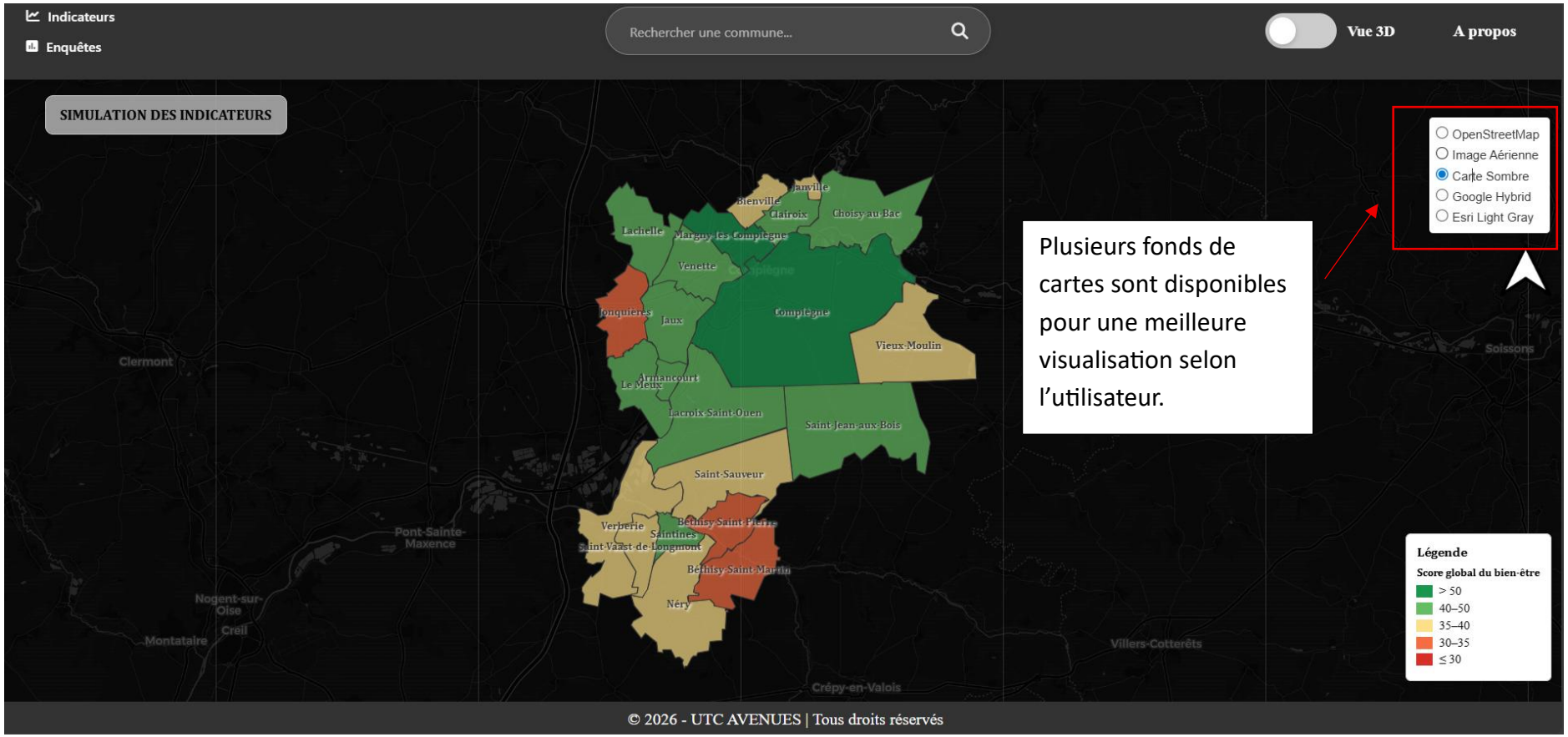

Visualisation 3D du territoire

Permet à l'utilisateur de visualiser le territoire avec plus de détails comme les bâtiments, les arbres ou encore les routes d'une manière plus visible. Pour activer ou désactiver cette fonctionnalité il suffit de switcher le bouton 3D.

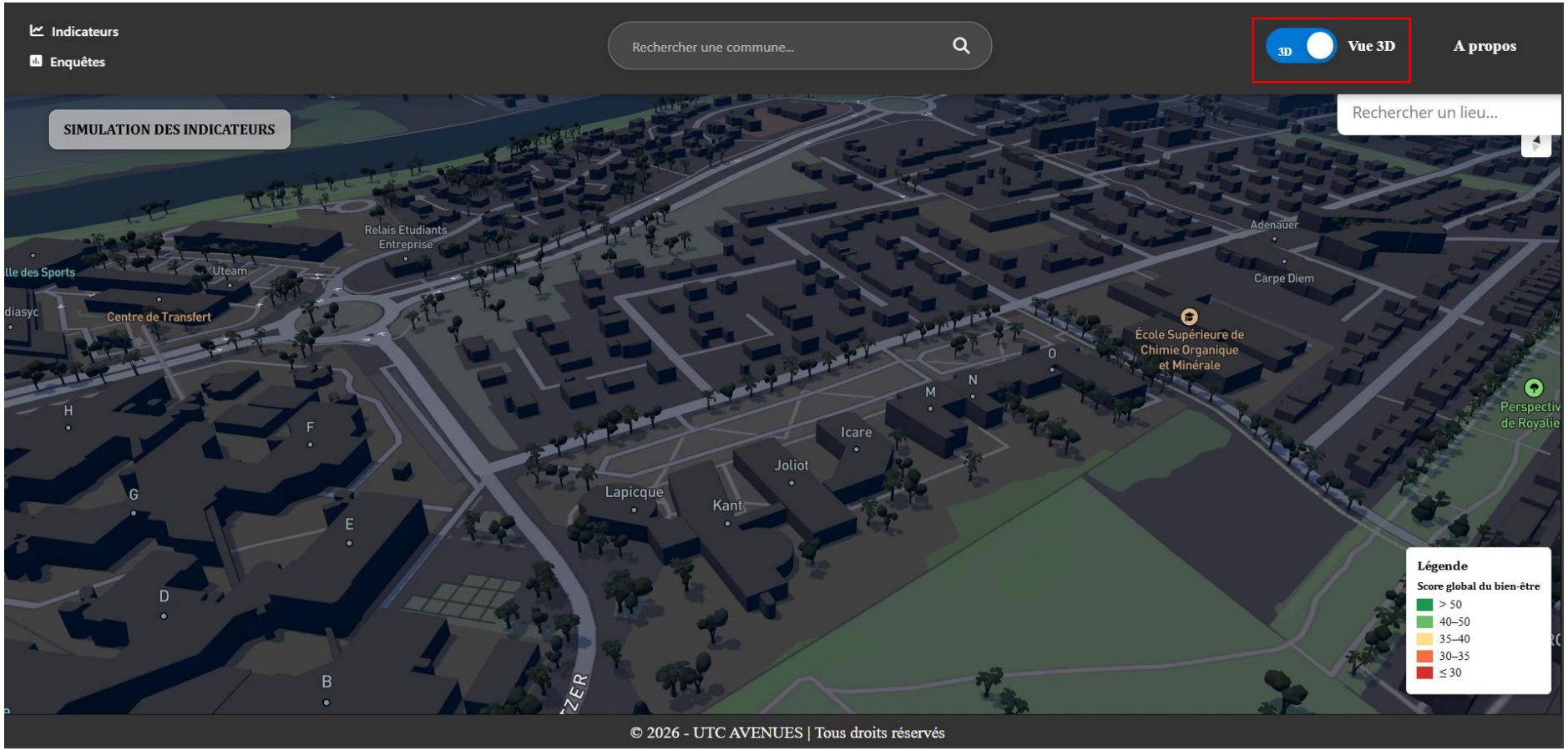

Lien de l’outil : https://mates.short.gy/sNATrd